Agrimensor Nacional Rodolfo Oscar Ferro
Av. Maipú N° 382 – Corrientes Capital
T. E. N° 0379-4460466 - 154687152 - oferro@hotmail.com
email: oferro@hotmail.com

INFORME

Atento a lo solicitado por el Contador Público Nacional Federico Diarte en Fecha 29/11/2022, se remite el presente Informe.

INFORME DEL DOMINIO CATASTRAL
Partida Inmobiliaria (Adrema): A1-45427-1 (s/Catastro Provincial)
Parcela N° 17
Manzana N° 15-C
Mensura N° 4147-U
Superficie: 242,17 m²
Calle: Guadalagara N° 265 (s/Catastro Municipal)
Barrio: Apipé.

INFORME DEL DOMINIO REGISTRAL
Propiedad de: Constructora EVISA S.A.
Inscripción Registro de la Propiedad Inmueble: Folio Real Matrícula N° 15328 - Año 1984.
(Datos extraídos de antecedentes de la Dirección General de Catastro Provincial)

DESCRIPCIÓN Y UBICACIÓN DEL INMUEBLE
El Inmueble se encuentra ubicado en el Barrio Apipé, sobre la calle Guadalajara N° 265, en la Parcela N° 17 de la Mz. N° 15-C (s/Mensura N° 4147-U), entre las calles: Sicilia al Norte y Argerich al Sur, en frente a una Reserva Municipal.
Dicho Inmueble consta de las siguientes medidas lineales:
9,57 metros de frente al Oeste y 9,57 metros de contrafrente al Este, por 25,22 metros de fondo al norte y 25,39 metros de contrafondo al Sur, con una superficie de 242,17 m².

Linderos:
Norte: Parcela N° 18, propiedad de Zulma Elena Aguirre.
Sur: Parcela N° 16, propiedad de Juana Delgado.
Este: Guaraní S.A.C.I.F.I. y E.
Oeste: Calle Guadalajara.

Ubicación con respecto a las esquinas:
28,72 metros al Norte, hacia calle Sicilia.
61,71 metros al Sur, Hacia calle Argerich.

Rodolfo Oscar Ferro
Agrimensor Nacional

Escaneado con CamScanner

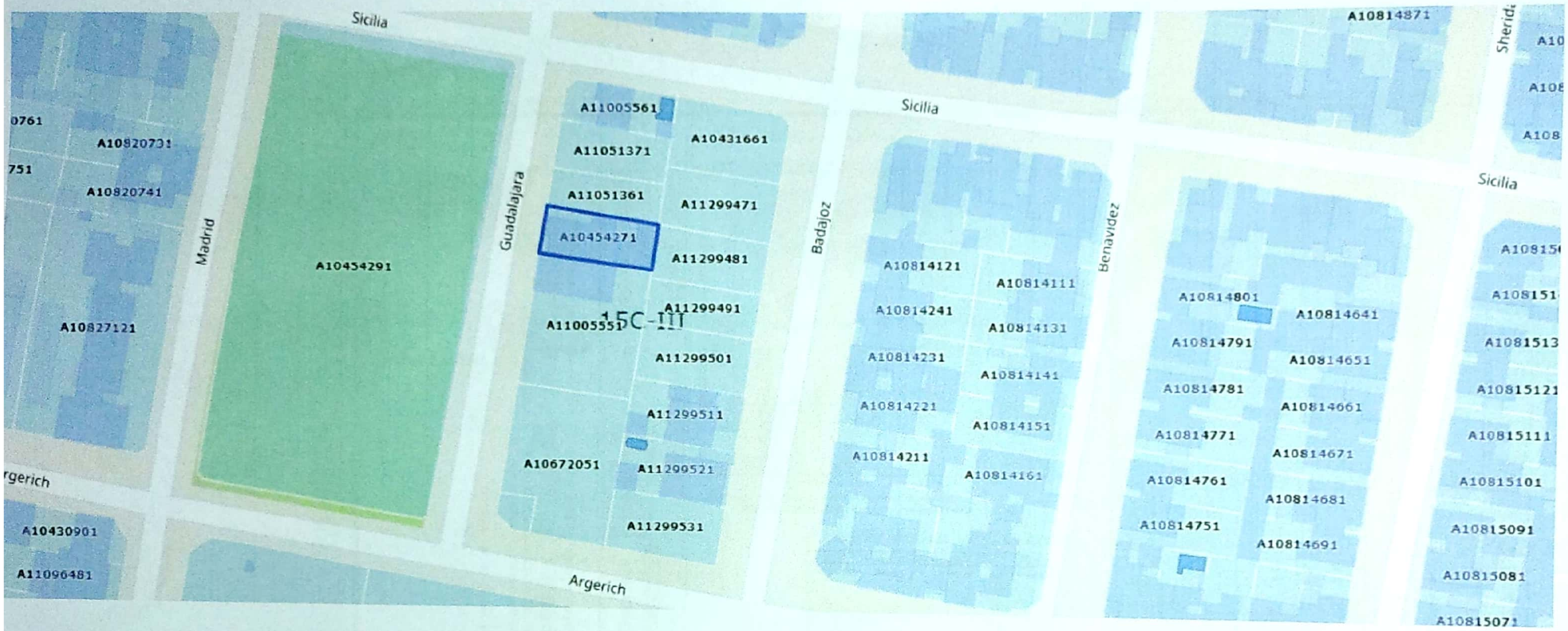
Sicilia
Sicilia
Sicilia
Madrid
Guadalajara
Badajoz
Benavidez
Argerich
A10820731
A10820741
A10827121
A10454291
A11005561
A11051371
A11051361
A10454271
A11005551
A10431661
A11299471
A11299481
A11299491
A11299501
A11299511
A11299521
A11299531
A10672051
A10430901
A11096481
A10814121
A10814111
A10814241
A10814131
A10814231
A10814141
A10814221
A10814151
A10814211
A10814161
A10814871
A10814801
A10814641
A10814791
A10814651
A10814781
A10814661
A10814771
A10814671
A10814761
A10814681
A10814751
A10814691
A10815121
A10815111
A10815101
A10815091
A10815081
A10815071
15C-III

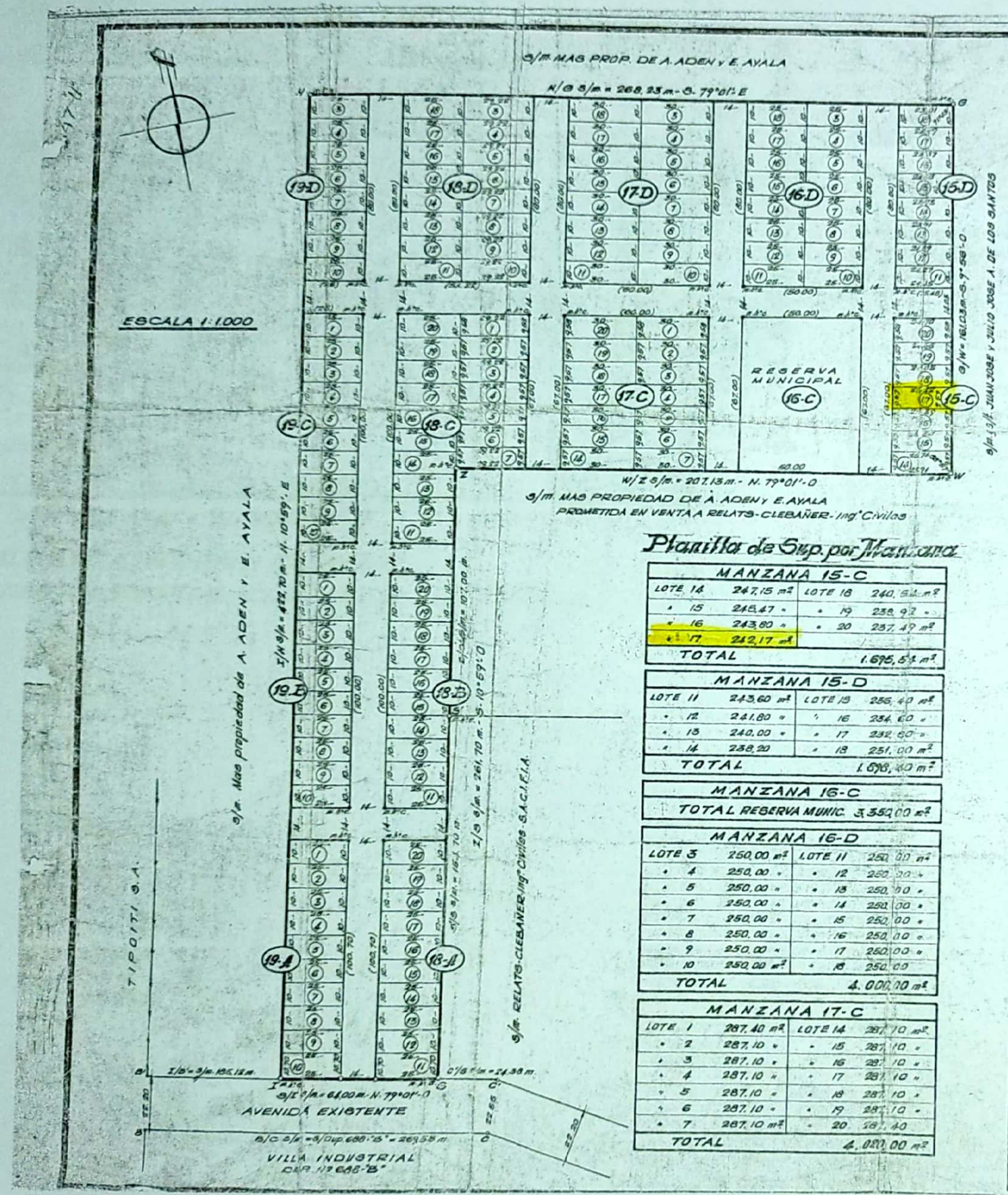

Planilla de Sup. por Manzana

MANZANA 15-C			
LOTE 14	247,15 m²	LOTE 18	240,54 m²
" 15	245,47 "	" 19	238,92 "
" 16	243,80 "	" 20	237,49 m²
" 17	242,17 m²		
TOTAL			1.695,54 m²

MANZANA 15-D			
LOTE 11	243,60 m²	LOTE 13	256,40 m²
" 12	241,80 "	" 16	254,60 "
" 13	240,00 "	" 17	252,80 "
" 14	238,20	" 18	251,00 m²
TOTAL			1.698,40 m²

MANZANA 16-C
TOTAL RESERVA MUNIC. 3.552,00 m²

MANZANA 16-D			
LOTE 3	250,00 m²	LOTE 11	250,00 m²
" 4	250,00 "	" 12	250,00 "
" 5	250,00 "	" 13	250,00 "
" 6	250,00 "	" 14	250,00 "
" 7	250,00 "	" 15	250,00 "
" 8	250,00 "	" 16	250,00 "
" 9	250,00 "	" 17	250,00 "
" 10	250,00 m²	" 18	250,00
TOTAL			4.000,00 m²

MANZANA 17-C			
LOTE 1	287,40 m²	LOTE 14	287,10 m²
" 2	287,10 "	" 15	287,10 "
" 3	287,10 "	" 16	287,10 "
" 4	287,10 "	" 17	287,10 "
" 5	287,10 "	" 18	287,10 "
" 6	287,10 "	" 19	287,10 "
" 7	287,10 m²	" 20	287,40
TOTAL			4.080,00 m²

MANZANA 17-D			
LOTE 3	300,00 m²	LOTE 11	300,00 m²
" 4	300,00 "	" 12	300,00 "
" 5	300,00 "	" 13	300,00 "
" 6	300,00 "	" 14	300,00 "
" 7	300,00 "	" 15	300,00 "
" 8	300,00 "	" 16	300,00 "
" 9	300,00 "	" 17	300,00 "
" 10	300,00 m²	" 18	300,00 "
TOTAL			4.800,00 m²

MANZANA 18-A			
LOTE 11	267,50 m²	LOTE 16	250,00 m²
" 12	250,00 "	" 17	250,00 "
" 13	250,00 "	" 18	250,00 "
" 14	250,00 "	" 19	250,00 "
" 15	250,00 "	" 20	250,00 "
TOTAL			2.517,50 m²

MANZANA 18-B			
LOTE 11	250,00 m²	LOTE 16	250,00 m²
" 12	250,00 "	" 17	250,00 "
" 13	250,00 "	" 18	250,00 "
" 14	250,00 "	" 19	250,00 "
" 15	250,00 "	" 20	250,00 "
TOTAL			2.500,00 m²

MANZANA 18-C			
LOTE 1	279,95 m²	LOTE 13	250,00 m²
" 2	279,64 "	" 14	250,00 "
" 3	279,64 "	" 15	250,00 "
" 4	279,64 "	" 16	250,00 "
" 5	279,64 "	" 17	250,00 "
" 6	279,64 "	" 18	250,00 "
" 7	279,64 "	" 19	250,00 "
" 11	250,00 "	" 20	250,00 "
" 12	250,00 "		
TOTAL			4.457,77 m²

MANZANA 18-D			
LOTE 3	292,20 m²	LOTE 11	250,00 m²
" 4	292,20 "	" 12	250,00 "
" 5	292,20 "	" 13	250,00 "
" 6	292,20 "	" 14	250,00 "
" 7	292,20 "	" 15	250,00 "
" 8	292,20 "	" 16	250,00 "
" 9	292,20 "	" 17	250,00 "
" 10	292,20 "	" 18	250,00 "
TOTAL			4.357,60 m²

MANZANA 19-A			
LOTE 1	250,00 m²	LOTE 6	250,00 m²
" 2	250,00 "	" 7	250,00 "
" 3	250,00 "	" 8	250,00 "
" 4	250,00 "	" 9	250,00 "
" 5	250,00 "	" 10	267,50 "
TOTAL			2.517,50 m²

MANZANA 19-B			
LOTE 1	250,00 m²	LOTE 6	250,00 m²
" 2	250,00 "	" 7	250,00 "
" 3	250,00 "	" 8	250,00 "
" 4	250,00 "	" 9	250,00 "
" 5	250,00 "	" 10	250,00 "
TOTAL			2.500,00 m²

MANZANA 19-C			
LOTE 1	250,00 m²	LOTE 6	250,00 m²
" 2	250,00 "	" 7	250,00 "
" 3	250,00 "	" 8	250,00 "
" 4	250,00 "	" 9	250,00 "
" 5	250,00 "	" 10	250,00 "
TOTAL			2.500,00 m²

MANZANA 19-D			
LOTE 3	250,00 m²	LOTE 7	250,00 m²
" 4	250,00 "	" 8	250,00 "
" 5	250,00 "	" 9	250,00 "
" 6	250,00 "	" 10	250,00 "
TOTAL			2.000,00 m²

SUMA TOTAL DE 153 LOTES	43.094,41 m²
SUMA DE CALLES	17.072,87 "
TOTAL FRACCION "HGWZ51"	60.167,28 "
TOTAL FRACC. "HGWZ51" S/DUP. 4043-"U"	60.167,28 m²

NOTA:
Medidas en metros.-
Angulos no especific. rectos ó suplementarios.-
m.h°c. : Mojón hormigón colocado.-
m.h°e. : Mojón hormigón existente.-

Nota: Unificac. y División lote 1 Nº 3 de la Mza 19/B con el lote 11 de Manz. 19/A. Ver Plano Nº 8255-U.-

OBJETO: DIVISION DE LA FRACCION "HGWZ51" EN BASE AL DUPL. Nº 4043-"U"
CARACTER: PARTICULAR
PROVINCIA DE CORRIENTES - REP. ARG.
DEPARTAMENTO: CAPITAL
LUGAR: MUNICIPIO DE CORRIENTES
PROPIEDAD DE:
"GUADANI" S.A.C.I.F.I.A.
UBICACION: MANZANA Nº 20 - PARAJE "BAÑADO NORTE"
DOMINIO: Reg. Prop. Capital: T° 2 - F° 257 - Nº 239 - Año 1974.-
Reg. Prop. Municip.: T° 2 - L: 8 - F° 268 - Fol. 247 - Año 1974.-
ADREMA: A1-2186-2
Duplicado relacionado: Nº 4043-"U"

DUP. DE MENSURA: 4147-U-
NOM. CATASTRAL:

CROQUIS DE UBICACION

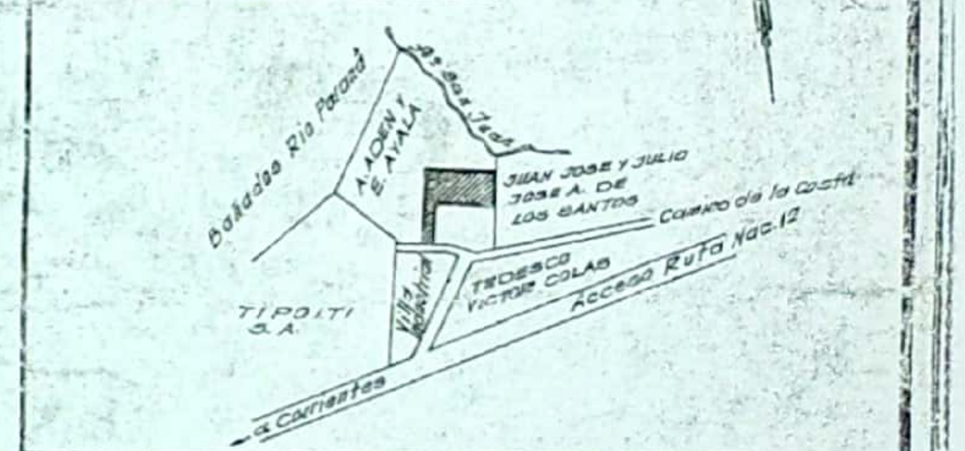

CORRIENTES, 23 DE DICIEMBRE DE 1975.-

AMERICO JACOBACCI
Agrimensor Nacional
Matric. Nº 147 - C. Prof. Nº 8
Dom.: Av. España 2302 - Ctes.-

JUAN CARLOS RELATS
Ingeniero Civil
L.E. Nº 6.011.183
por: Guadani S.A.C.I.F.I.A.

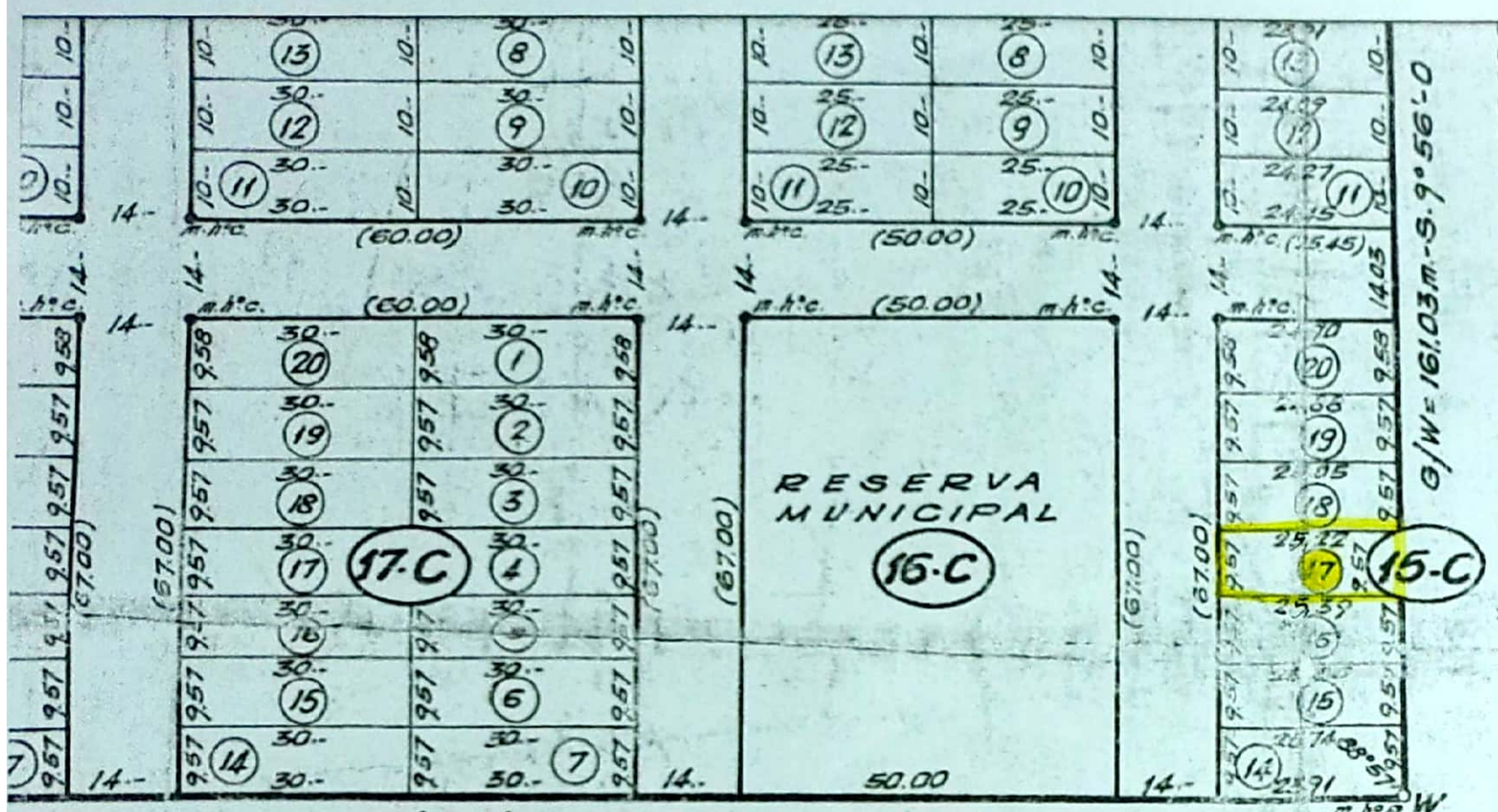

W/Z S/m. = 207.13 m.- N. 79°01'-O

S/m. MAS PROPIEDAD DE A. ADEN y E. AYALA

PROMETIDA EN VENTA A RELATS-CLEBAÑER-Ing.° Civiles

MANZANA 18-A

LOTE 11	267.50 m²	LOTE 16	250.00 m²
" 12	250.00 "	" 17	250.00 "
" 13	250.00 "	" 18	250.00 "
" 14	250.00 "	" 19	250.00 "
" 15	250.00 "	" 20	250.00 "
TOTAL			2.517.50 m²

MANZANA 18-B

LOTE 11	250.00 m²	LOTE 16	250.00 m²
" 12	250.00 "	" 17	250.00 "
" 13	250.00 "	" 18	250.00 "
" 14	250.00 "	" 19	250.00 "
" 15	250.00	" 20	250.00
TOTAL			2.500.00 m²

MANZANA 18-C

LOTE 1	279.93 m²	LOTE 13	250.00 m²
" 2	279.64 "	" 14	250.00 "
" 3	279.64 "	" 15	250.00

Dirección General de Catastro y Cartografía
Ministerio de Hacienda y Finanzas
Gobierno de Corrientes

Reporte Unidad Tributaria

Partida Inmobiliaria
A10454271

Datos Generales

Tipo Unidad	Unidad Funcional	Piso	Unidad
COMUN	-	-	-

% de Copropiedad	Fecha Alta	Fecha Baja
0.0	**27/09/2011**	-

Dominios

Tipo	Inscripción	Año
MATRICULA	**0000015328/1984**	**1984**

Titulares

Nombre Completo	Tipo y Nro.	% de Copropiedad
S.A.CONSTRUCTORA EVISA	**DOCUMENTO FICTICIO/100003583**	**100.0**

Valuación

Fecha de Vigencia	Valor de la Tierra	Valor Mejoras	Valor Total
01/09/2009	**$ 852,65**	**$ 0,00**	**$ 852,65**

Observaciones

Sin Observaciones

Escaneado con CamScanner