INFORME DE VALUACIÓN

RESUMEN EJECUTIVO

Santa Fe Nº987 – Local 7 – Ciudad de Corrientes
Tel (0379) 44 66 044 Móvil (0379) 15 422 8799
armandovallejos.com.ar

INMUEBLE

CALLE 511 s/Nº
Barrio Sin Nombre (Entre Zona Sur Pirayuí y Zona Sur Ponce)
Ciudad de Corrientes

FECHA

8 de marzo de 2025

VALOR DE MERCADO

$18.000.000.-

Precio más probable que se pagará por el inmueble en el mercado local en la fecha del informe

Cotización dólar **BNA**: $1.035,13 / $1.094,53 **Blue**: $1.195,00 / $1.215,00

TASADOR

Sebastián Armando Vallejos
Martillero y Corredor
MP 11 CPMyC
CUIT 20184413109

I. DATOS GENERALES DE LA TASACIÓN

COMITENTE	Nombre o Razón Social: Síndico Cdor RAMÓN R. ZACARIAS	
	Domicilio: Brasil 1420	
	Departamento: Capital	Provincia: Corrientes
	Mail: - - -	Teléfono: - - -
TASADOR	Nombre: SEBASTIÁN ARMANDO VALLEJOS	
	Profesión: PERITO TASADOR	Matrículas: Nº 27 S.T.J. Colegiado Nº 11
	Domicilio: SANTA FE 987 LOCAL 7	Teléfono: 0379 446 6044
	Mail: contacto@armandovallejos.com	

MOTIVO DE LA TASACIÓN

~~ANÁLISIS DE COMPRA-VENTA~~	~~EFECTO SOCIETARIO~~	~~PERMUTA, DACIÓN O TRANSF.~~	~~CRÉDITO HIPOTECARIO~~
~~INVENTARIO PATRIMONIAL~~	~~EFECTO IMPOSITIVO~~	~~PARTICIÓN HEREDITARIA~~	~~ANÁLISIS DE INVERSIÓN~~
~~PERICIA JUDICIAL O SUBASTA~~	~~EFECTO LOCATIVO~~	~~AVALUÓ EN SEGUROS~~	**OTROS**

DIRECCIÓN DE LA PROPIEDAD	Calle: **Calle 511 s/Nº**			
	Entre las calles: Arroyo Pirayui y calle 204			
	Mblock: - -	Piso: - -	Dpto: - -	Mensura: 6146-U
	Mz: 39	Lote: 1	Localidad: Corrientes	
	Departamento: Capital	Provincia: Corrientes	CP: 3400	
	Coordendas Geográfica de Ubicación: -27° 30' 18",-58° 46' 6.60"			

II. DATOS GENERALES DEL INMUEBLE

Nomenclatura Catastral: ADREMA A1-052017-1 (En Mayor Extensión)
Inscripción en el Registro de la Propiedad Inmueble: - - -

Titular Registral: No suministrado

Documentación Adjunta:
PARTIDA INMOBILIARIA

TIPOLOGÍA

FRACCIÓN DE TIERRA LIBRE DE CONSTRUCCIONES

~~COCHERA~~	~~GALPÓN~~
~~DEPARTAMENTO~~	~~EDIFICIO INDUSTRIAL~~
~~CASA~~	~~DOS O MAS PLANTAS~~
~~LOCAL COMERCIAL~~	~~DÚPLEX~~
~~OFICINA~~	~~OTROS:~~

DESTINO

~~HABITACIÓN~~
~~COMERCIAL~~
~~PROFESIONAL~~
~~INDUSTRIAL~~

ESTADO DE OCUPACIÓN

~~OCUPADO~~
DESOCUPADO

USO

~~PERMANENTE~~ ~~TEMPORARIO~~

CARACTERÍSTICA DE LA ZONA

~~URBANA~~ **SUBURBANA**

DEUDAS CONOCIDAS
MUNICIPALIDAD: N/A
CO.VE.SA: N/A
OTRAS:

GRAVÁMENES CONOCIDOS
N/A

III. DETALLE DEL TERRENO

FRENTE	C/FRENTE	FONDO	C/FONDO	SUPERFICIE TOTAL			
19,10	13,75	50	50,29	821,25 m2	**SEGÚN PLANO**	~~SEGÚN TITULO~~	~~SEGÚN CATASTRO~~

Dimensiones Perimetrales (Para terrenos irregulares): N/A

Observaciones: N/A

SUELO

SECO Y FIRME	~~INUNDABLE LEVE Y POR TRAMOS~~
~~RELLENADO~~	~~ANEGADO~~
~~HÚMEDO~~	~~PANTANOSO~~

FORMA

~~RECTANGULAR~~	**IRREGULAR**
~~MARTILLO +~~	~~MARTILLO –~~
~~LEVEMENTE IRREGULAR~~	

PLANEAMIENTO URBANO

AUTORIDAD DE CONTRALOR: MUNICIPALIDAD DE SANTA ANA DE LOS GUÁCARAS

DISTRITO: - - - FOS: - - - FOT: - - -

ORIENTACIÓN	VISTA	POSICIÓN DEL LOTE	
		EN LA MANZANA	EN LA CUADRA
~~NORTE~~ ~~SUR~~	~~FAVORABLE~~ ~~VISTA IMPORTANTE~~	~~INTERNO~~	~~ESQUINA~~
~~ESTE~~ **OESTE**	~~DESFAVORABLE~~ **POCA VISTA**	**EXTERNO**	**MEDIAL**

NIVEL DEL TERRENO RESPECTO A LA CALLE

~~ALTO~~
NORMAL
~~BAJO~~

INFRAESTRUCTURA Y SERVICIOS

ALUMBRADO PUBLICO
AGUA CORRIENTE
~~PAVIMENTO ASFALTICO~~
~~VIGILANCIA~~
~~RECOLECCIÓN DE RESIDUOS~~
~~RED DE CLOACAS~~
~~RED DE VIDEO-CABLE~~
~~TRANSPORTE PUBLICO~~
~~RED TELEFÓNICA~~
RIPIO O MEJORA DE CALLE

ENTORNO

CARACTERÍSTICA DEL ÁREA
Viviendas unifamiliares.

TIPOLOGÍA DE LAS CONSTRUCCIONES
Tradicional.

CALIDAD EDILICIA DEL ÁREA
Buena

CALIDAD URBANA DEL ÁREA
Buena

DENSIDAD POBLACIONAL
30%

NIVEL SOCIO-ECONÓMICO
Medio

ELEMENTOS MODIFICATORIOS DEL ESPACIO URBANO
No se observa.

CICLO VITAL DEL VECINDARIO
Estable.

VECINOS
Sin influencia.

IV. DETALLE DE LA EDIFICACIÓN

DIMENSIONES (solo totales)

	SUP. CUBIERTA			SUP. SEMICUBIERTA			SUP. MEJORADA		
CONSTRUCCIÓN	**PLANO**	**RELEV.**	**ESTIMA.**	**PLANO**	**RELEV.**	**ESTIMA.**	**PLANO**	**RELEV.**	**ESTIMA.**
~~CASA~~	~~m2~~	~~m2~~	~~m2~~	~~m2~~	~~m2~~	~~m2~~	~~m2~~	~~m2~~	~~m2~~
~~QUINCHO~~	~~m2~~	~~m2~~	~~m2~~	~~m2~~	~~m2~~	~~m2~~	~~m2~~	~~m2~~	~~m2~~
~~PILETA~~	~~m2~~	~~m2~~	~~m2~~	~~m2~~	~~m2~~	~~m2~~	~~m2~~	~~m2~~	~~m2~~
~~GALPÓN~~	~~m2~~	~~m2~~	~~m2~~	~~m2~~	~~m2~~	~~m2~~	~~m2~~	~~m2~~	~~m2~~
~~PLAYA DE MANIOBRAS~~	~~m2~~	~~m2~~	~~m2~~	~~m2~~	~~m2~~	~~m2~~	~~m2~~	~~m2~~	~~m2~~

SITUACIÓN
CONSTRUIDO ~~EN CONSTRUCCIÓN (EJECUCIÓN ESTIMADA: %)~~ ~~EN REPARACIÓN: m2 a reparar~~

TIPO DE EDIFICACIÓN

PAREDES	FACHADA (ext.)	REVESTIMIENTO	TECHOS	PISOS	CIELORRASOS
- - -	- - -	- - -	- - -	- - -	- - -
ABERTURAS	VENTANAS	PUERTAS	ESCALERA	BAÑOS	COCINA
- - -	- - -	- - -	- - -	- - -	- - -

OBSERVACIONES:

FUNCIONALIDAD

~~MUY BUENA DISTRIBUCIÓN~~
~~BIEN DISTRIBUIDA, CON ALGUNA LIMITACIÓN~~
~~REGULAR DISTRIBUCIÓN, CON LIMITACIONES IMPORTANTES~~
~~MAL DISTRIBUIDA~~

~~BUENA ILUMINACIÓN~~
~~ESCASA ILUMINACIÓN NATURAL~~

~~ADECUADA VENTILACIÓN~~
~~ESCASA VENTILACIÓN~~

CALIDAD DE MATERIALES

~~MUY BUENA~~ ~~NORMAL (LÍNEA ESTÁNDAR)~~ ~~BAJA (LÍNEA ECONÓMICA)~~

CALIDAD CONSTRUCTIVA

~~MUY BUENA~~ ~~REGULAR~~
~~BUENA~~ ~~MALA~~

NIVEL DE TERMINACIONES

~~MUY PROLIJAS~~ ~~BIEN EJECUTADAS~~ ~~SENCILLAS~~ ~~MAL REALIZADAS~~

ANTIGÜEDAD

REAL (SI CONOCE): N/A	ORIGEN DEL DATO: - - -
ESTIMADA: - - -	ORIGEN DEL DATO: - - -
VIDA REMANENTE: N/A	FUNDAMENTACIÓN: - - -

ESTADO DE CONSERVACIÓN

~~NUEVO~~
~~ENTRE NUEVO Y NORMAL~~
~~NORMAL~~
~~ENTRE NORMAL Y NECESITA REPAROS SIMPLES~~
~~NECESITA REPAROS SIMPLES~~
~~ENTRE NECESITA REPAROS SIMPLES E IMPORTANTES~~
~~NECESITA REPAROS IMPORTANTES~~
~~ENTRE NECESITA REPAROS IMPORTANTES Y OBSOLETO~~
~~OBSOLETO~~

COMPOSICIÓN AMBIENTAL

HABITACIÓN			
DORMITORIOS EN SUITE	0	DEPENDENCIAS DE SERV.	0
DORMITORIOS	0	SALA DE USOS MÚLTIPLES	0
BAÑOS	0	LAVADERO	0
COCINA	0	DEPÓSITO	0
COCINA COMEDOR	0	PATIO	0
COMEDOR	0	QUINCHO	0
ESTAR – COMEDOR	0	TERRAZA	0
ESTAR	0	BALCÓN	0
SALA DE ESTUDIOS	0	SÓTANO	0
GARAJE – COCHERA	0	OTRAS	-

COMERCIO, INDUSTRIA, SERVICIOS			
0	SALON	0	VESTUARIO
0	DEPÓSITO	0	BAÑOS
0	GALPÓN	0	PORTERÍA
0	TINGLADO	0	PLAYA

SERVICIOS Y COMODIDADES

ENERGÍA ELÉCTRICA MONOFÁSICA
~~ENERGÍA ELÉCTRICA TRIFÁSICA~~
AGUA POTABLE DE RED
~~AGUA DE POZO~~
~~GAS NATURAL DE RED~~
~~DESAGÜE CLOACAL A RED~~
~~DESAGÜE CLOACAL A POZO ABSORBENTE~~
~~AGUA CALIENTE~~
~~TELÉFONO~~
~~AIRE ACONDICIONADO INDIVIDUAL~~
~~PLACARD EN DORMITORIO~~
~~MUEBLES DE COCINA~~
~~BAÑO COMPLETO~~
~~HIDROMASAJE~~
~~SAUNA~~
~~PORTERO ELÉCTRICO~~
~~SEGURIDAD ELECTRÓNICA~~
~~VIGILANCIA~~
~~HOGAR A LEÑOS~~
~~ASCENSOR~~

	~~AIRE ACONDICIONADO CENTRAL~~ ~~CALEFACCIÓN INDIVIDUAL~~ ~~CALEFACCIÓN CENTRAL~~ ~~PILETA DE NATACIÓN~~ ~~GRUPO ELECTRÓGENO~~ ~~JARDÍN PARQUIZADO~~
SERVICIOS Y COMODIDADES (escala, calles y orientación)	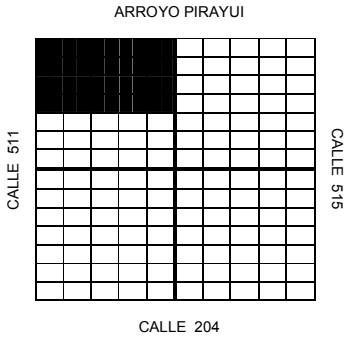

CARACTERÍSTICAS ADVERSAS/DEFICIENCIAS:
N/A

DESCRIPCIÓN DEL COMERCIO, INDUSTRIA O SERVICIOS:
N/A

BREVE DESCRIPCIÓN DE MEJORAS PREVISTAS:
N/A

DESCRIPCIÓN DE LA ZONA MEJORADA:
N/A.

OBSERVACIONES GENERALES:
N/A

V. MÉTODO DE TASACIÓN e INFORME DEL VALOR

MÉTODO DE SELECCIÓN:

COMPARATIVO DE MERCADO ~~POR COSTO DE REPOSICIÓN DEPRECIADO~~ ~~ESTIMACION~~

~~POR CÁLCULO DE COSTOS~~ ~~POR CAPITALIZACIÓN DE RENTAS~~

CARACTERÍSTICAS VENTAJOSAS: Sin comentarios.

CARACTERÍSTICAS DESVENTAJOSAS/ADVERSAS: Sin comentarios.

INFORME DEL VALOR	TERRENO	$ 18.000.000.-
	EDIFICACIÓN	$ 0.-
	COEFICIENTE FC	1,00
	VALUACIÓN	**$ 18.000.000.- (Pesos Dieciocho millones)**

FIRMA Y SELLO DEL TASADOR	FIRMA Y SELLO DEL AUDITOR	PERIODO DE VALIDEZ 60 (SESENTA) DÍAS

VI. REFERENCIAS

Se debe llenar el espacio vacío, tachar en el cuadro pertinente las opciones deseadas o tachar la palabra que no corresponda.
Los paréntesis con espacio intermedio en blanco requieren expresión de cantidad o descripción.
Las medidas de longitud y superficie, y la antigüedad del edificio, de no contar con documentación que las informen: se relevan o estiman.
En caso de no disponerse de la información requerida se consignará “N/S” (desconozco), o se esta resulta irrelevante para la propiedad tasada, se consignará “N/A” (No aplicable).

VII. CERTIFICADO DE LABOR

1. Realicé esta tasación de conformidad con las normas de tasación aplicables a nuestro país.
2. Investigué el área y seleccioné –como antecedentes comparativos- un mínimo de tres ventas u ofertas recientes de propiedades similares y próximas al bien en cuestión.
3. Incorporé en el informe de tasación solo mi análisis, opiniones y conclusiones personales, que son imparciales y profesionales. Si me basé en la asistencia de algún profesional o profesionales en la preparación de la tasación o la confección del informe de tasación, certifico que las personas nombradas están capacitadas para realizar las tareas.
4. No tengo interés actual o probable en el bien objeto de este informe, y no tengo interés prejuicio personal actual o probable respecto a los participantes de la transacción.
5. No se me exigió informar un valor predeterminado ni ninguna tendencia en cuanto al valor que favoreciera la causa del cliente parte vinculada. No basé el informe de tasación en una valuación mínima requerida, una valuación específica, o la necesidad de aprobar un préstamo hipotecario.
6. No he ocultado en forma consciente ninguna información significativa en este informe y creo, según mi leal saber y entender, que toda información y declaración que figuran en el informe de tasación son fieles y correctas.

VIII. INFORMACIÓN ADJUNTA

~~TÍTULOS~~ ~~FOTOS~~

PLANOS ~~CROQUIS~~

OTROS: REPORTE PARCELARIO

PLANO DE UBICACIÓN

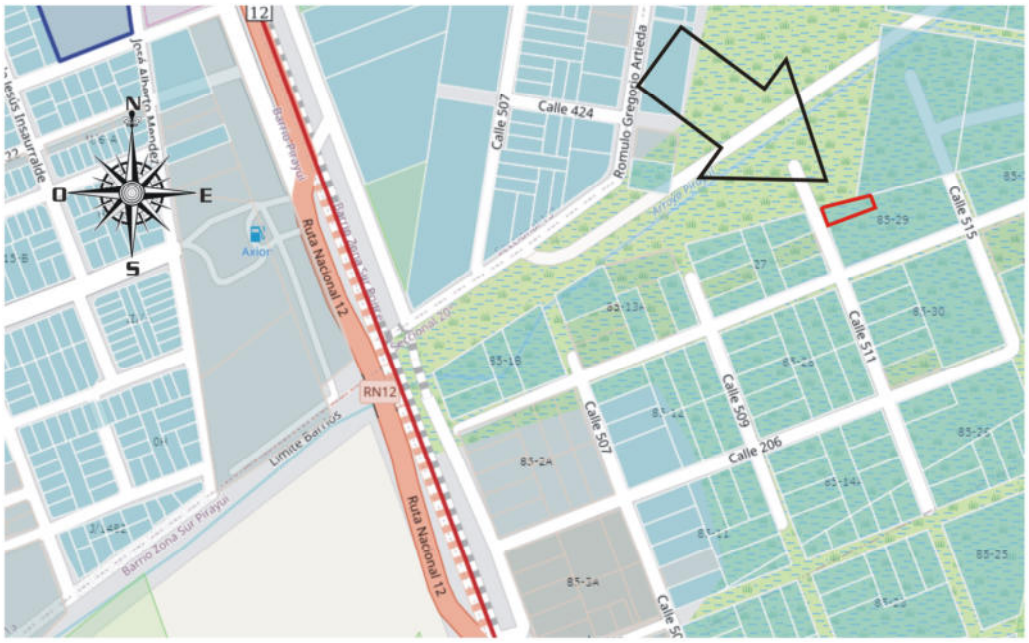

CROQUIS DE LA MENSURA

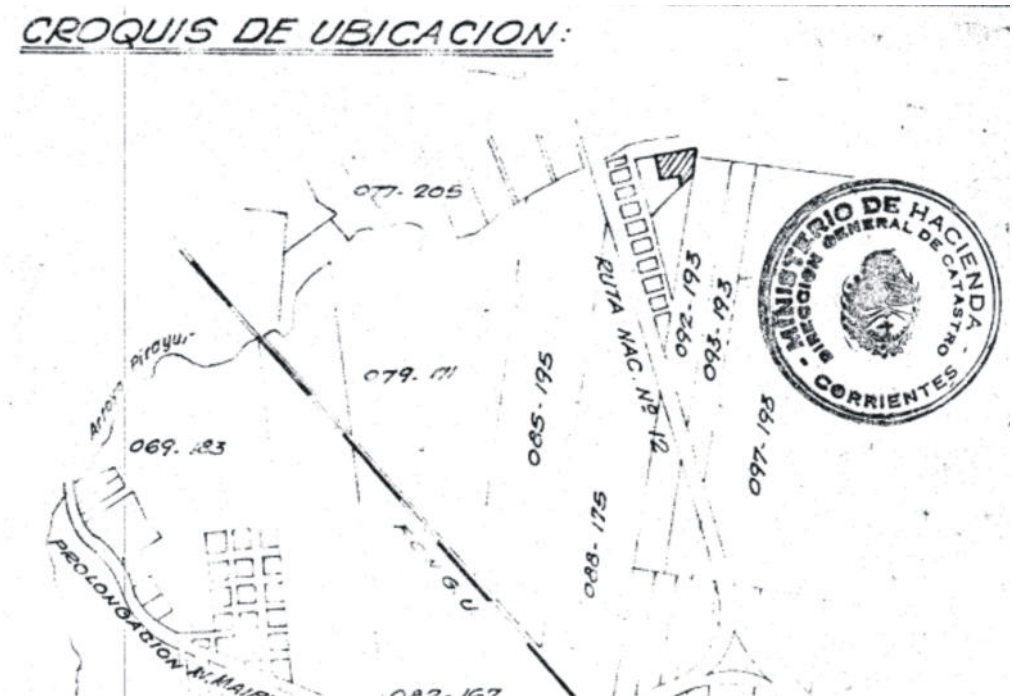

DETALLE DE LA MENSURA

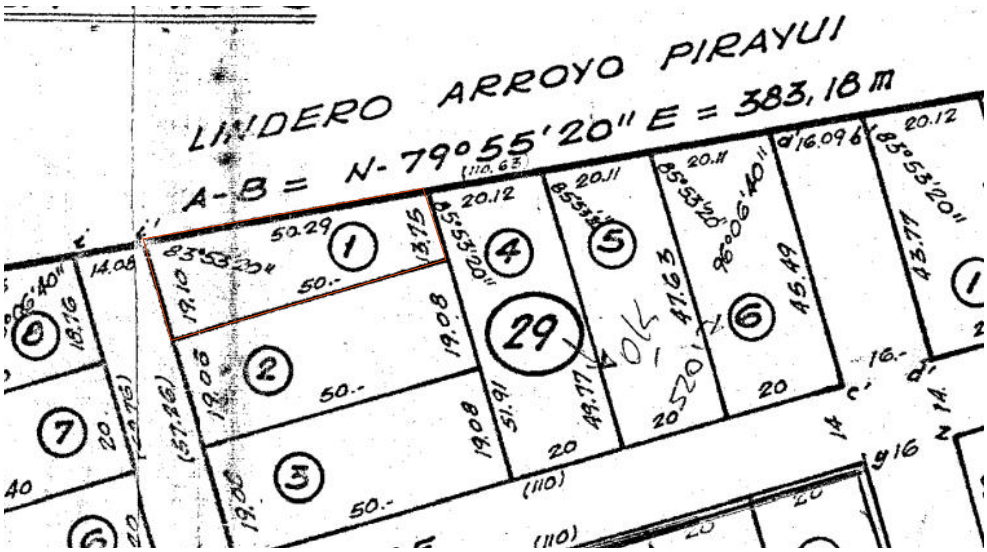

FOTOGRAFÍA AÉREA